Biblische Umwelt AT
Die Kulturen der antiken Levante und ihrer Nachbarn in Texten und Bildern

Frühlingssemester 2026

UniFr

PD Dr. theol. Thomas Staubli

Thema	Beschreibung/Unterlagen	Datum
	Die Welt der Bibel …im Kopf …in der Bibel …in der «Realität»	19.2.
	Baal-Zyklus TUAT 1091-1198 Keret-Epos TUAT 1213-53 Aqhat-Epos TUAT 1254-1305	5.3.
	Sinuhe TUAT 884-911 Zwei Brüder Wettengel, OBO 195 Wenamun TUAT 912-29	19.3.
	Enki und Ninmach TUAT 386-401 Enlil und Ninlil TUAT 421-33 Inannas Gang zur Unterwelt TUAT 458-94 Enuma Elisch TUAT 565-602 Gilgamesch TUAT 646-744	2.4.
	Telipinu-Mythen TUAT 811-20 Ullikummi-Lied TUAT 830-43 weitere	16.4.
	Hesiod, Theogonie Odyssee Ilias	30.4.
	700 Skarabäen: Die Sammlung Keel 700 Skarabäen_Tafeln 1-81	14.5.

Levante

EUROPA
ASIEN
Levante
AFRIKA

Schwarzes Meer
Kaspisches Meer
Mittelmeer
Persischer Golf
Rotes Meer
Indischer Ozean

Orontes
Tigris
Euphrat
Jordan
Nil

Tauros
Zagros
Libanon
Sinai

FRUCHTBARER HALBMOND

London
Berlin
Moskau
Paris
Wien
Rom
KGR. GROSSBRITANNIEN UND IRLAND
KGR. DÄNEMARK
SCHWEDEN
NORDSEE
OSTSEE
ATLANTISCHER OZEAN
KAISERREICH RUSSLAND
FRANKREICH
SCHWEIZ
KGR. BELGIEN
KGR. PORTUGAL
KGR. SPANIEN
KGR. GRIECHENLAND
SCHWARZES MEER
MITTELMEER
Kurland
Wolhynien
Podolien
Ukraine
Krim
Galizien
Böhmen
Siebenbürgen
Slawonien
Bosnien
Serbien
Bulgarien
Rumänien
Makedonien
Albanien
Korsika
Sardinien
Sicilien
Kreta
Kleinasien
Anatolien
Im Deutsch-Französischen Krieg von 1870/71 von dt. Truppen erobertes Gebiet
Kommune: Während des Krieges sozialist.-revolutionärer Stadtrat
des Deutschen Reiches 1871-1918
im Dt. Kaiserreich
Kaiserreich

FORO ROMANO
Rom
Im Deutsch-Französischen Krieg von 1870/71 von dt. Truppen erobertes Gebiet
Pariser Kommune: Während des Kriegs errichteter sozialist.-revolutionärer Stadtrat
Grenze des Deutschen Reiches 1871-1918
Königreich Preußen im Dt. Kaiserreich
Andere Staaten im Dt. Kaiserreich
ATLANTISCHER OZEAN
SCHWARZES MEER
KGR. GROSSBRITANNIEN UND IRLAND
Dublin
Cork
Guernsey
Jersey
Brest
Nantes
Bordeaux
La Coruña
Oviedo
Burgos
Vitoria
Pamplona
Bayonne
Toulouse
Porto
Salamanca
Zaragoza
Madrid
Barcelona
Lissabon
Badajoz
Toledo
Aranjuez
Valencia
Sevilla
Bailen
Granada
Gibraltar
Torres Vedras
KGR. PORTUGAL
KGR. SPANIEN
Rep. Andorra
Marseille
Toulon
Fsm. Monaco
Genua
Livorno
Florenz
Bologna
Rep. San Marino
Korsika
Ajaccio
Sardinien
Cagliari
Palermo
Messina
Tarent
Brindisi
Korfu
Ionisches Meer
Balearen
Menorca
Mallorca
Ibiza
MITTELMEER
Belgrad
Serbien tributpflichtige Fsm.
Bosnien
Nisch
Sofia
Bulgarien
Cattaro
Albanien
Adrianopel
Konstantinopel
Makedonien
Saloniki
Lesbos
Chios
Samos
Athen
KGR. GRIECHENLAND
Warna
Sinope
Angora
Brussa
Adalia
Kiew
Jekaterinoslaw
Ukraine
Odessa
Cherson
Krim
Sewastopol
Kaukasus
1828-1856 russ.
1856-1878 osm.

Berlin
Im Deutsch-Französischen Krieg von 1870/71 von dt. Truppen erobertes Gebiet
Pariser Kommune: Während des Kriegs errichteter sozialist.-revolutionärer Stadtrat
Grenze des Deutschen Reiches 1871-1918
Königreich Preußen im Dt. Kaiserreich
Andere Staaten im Dt. Kaiserreich
KGR. GROSSBRITANNIEN UND IRLAND
KGR. DÄNEMARK
SCHWEDEN
NORDSEE
OSTSEE
ATLANTISCHER OZEAN
KGR. NIEDERLANDE
KGR. BELGIEN
DEUTSCHES KAISERREICH
RUSSLAND
Kurland
Ukraine
Krim
SCHWARZES MEER
KGR. PORTUGAL
KGR. SPANIEN
Berlin Blick vom Brandenburger Tor auf die Siegessäule

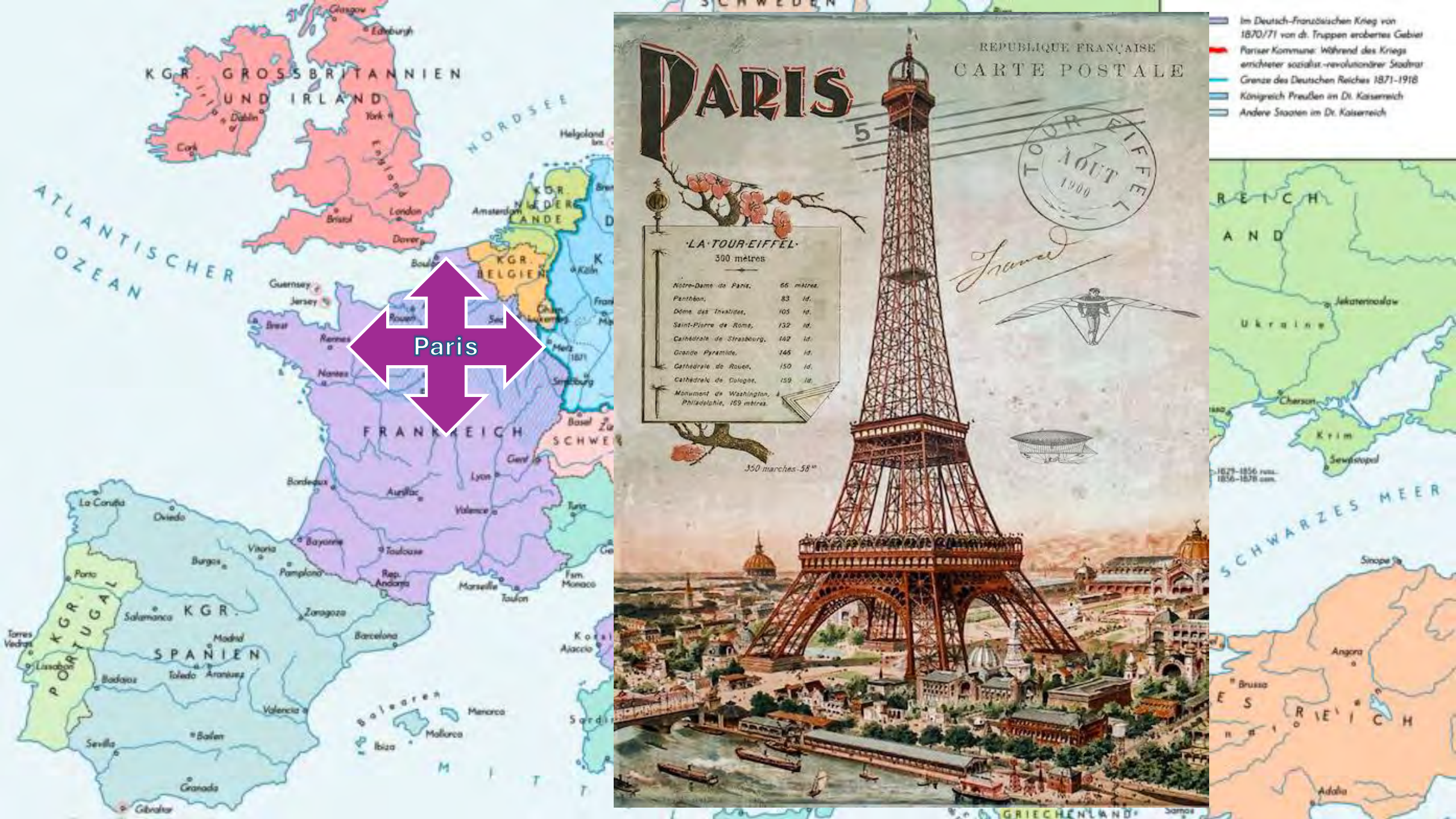
Paris
KGR. GROSSBRITANNIEN UND IRLAND
NORDSEE
ATLANTISCHER OZEAN
KGR. NIEDERLANDE
KGR. BELGIEN
FRANKREICH
KGR. SPANIEN
KGR. PORTUGAL
SCHWARZES MEER
REPUBLIQUE FRANÇAISE
CARTE POSTALE
PARIS
·LA·TOUR·EIFFEL·
300 mètres
TOUR EIFFEL
AOUT
1900
Im Deutsch-Französischen Krieg von 1870/71 von dt. Truppen erobertes Gebiet
Pariser Kommune: Während des Kriegs errichteter sozialist.-revolutionärer Stadtrat
Grenze des Deutschen Reiches 1871-1918
Königreich Preußen im Dt. Kaiserreich
Andere Staaten im Dt. Kaiserreich

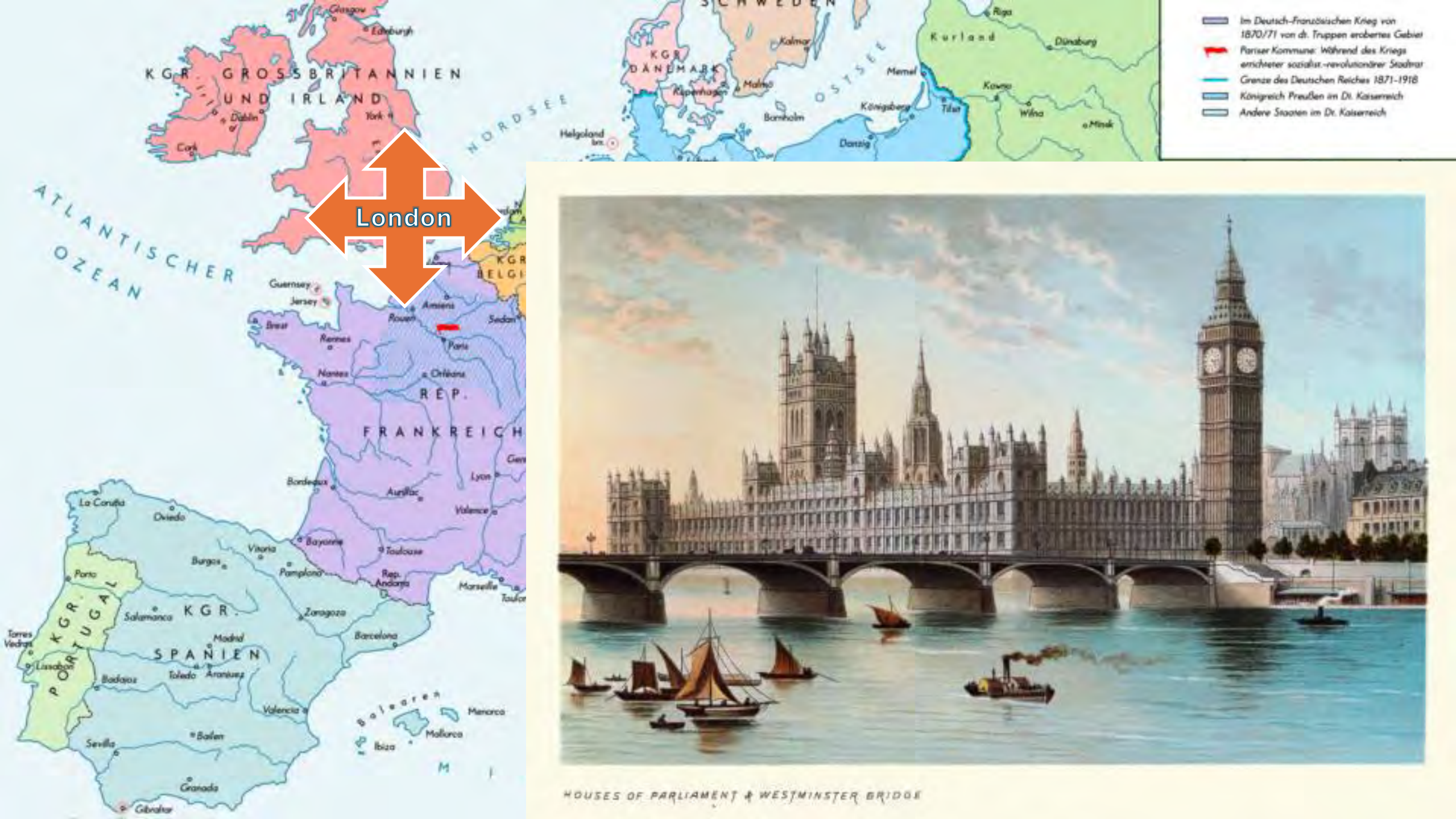
London
KGR. GROSSBRITANNIEN UND IRLAND
Glasgow
Edinburgh
Dublin
Cork
York
NORDSEE
ATLANTISCHER OZEAN
Guernsey
Jersey
Brest
Rennes
Nantes
Rouen
Amiens
Paris
Orléans
Sedan
KGR. BELGIEN
REP. FRANKREICH
Bordeaux
Auxillac
Lyon
Valence
Bayonne
Toulouse
Rep. Andorra
Marseille
Toulon
La Coruña
Oviedo
Vitoria
Burgos
Pamplona
Porto
KGR. PORTUGAL
Salamanca
KGR. SPANIEN
Zaragoza
Barcelona
Madrid
Toledo
Aranjuez
Badajoz
Lissabon
Torres Vedras
Valencia
Balaren
Menorca
Mallorca
Ibiza
Sevilla
Bailen
Granada
Gibraltar
SCHWEDEN
Kalmar
KGR. DÄNEMARK
Malmö
Kopenhagen
Bornholm
OSTSEE
Helgoland
Memel
Königsberg
Tilsit
Danzig
Riga
Kurland
Dünaburg
Kowno
Wilna
Minsk
Im Deutsch-Französischen Krieg von 1870/71 von dt. Truppen erobertes Gebiet
Pariser Kommune: Während des Kriegs errichteter sozialist.-revolutionärer Stadtrat
Grenze des Deutschen Reiches 1871-1918
Königreich Preußen im Dt. Kaiserreich
Andere Staaten im Dt. Kaiserreich
HOUSES OF PARLIAMENT & WESTMINSTER BRIDGE

FORO ROMANO

Hattuscha
Assur
Babylon
Memphis
Persepolis

Berlin Blick vom Brandenburger Tor auf die Siegessäule

PARIS
REPUBLIQUE FRANÇAISE
CARTE POSTALE
LA TOUR EIFFEL
300 mètres

HOUSES OF PARLIAMENT & WESTMINSTER BRIDGE

Hattuscha

HETHITER

ASSYRER

Assur

BABYLONIER

Babylon

PERSER

Persepolis

Memphis

ÄGYPTER

ROM

WASHINGTON

Hattuscha

HETHITER

ASSYRER

Assur

BABYLONIER

Babylon

PERSER

Persepolis

Memphis

ÄGYPTER

PARIS

VATIKAN

LONDON

Imperiale Obeliskomanie

Imperiale Schatzkammern

Hattuscha
Jamchad
(Aleppo)
Ugarit
Ebla
Assur
Kition
Hama
(Larnaka)
Qatna
Tadmor (Palmyra)
Byblos
Mari
Sidon
Damaskus
Tyros
Samaria
Babylon
Aschkelon
Amman
Gaza
Jerusalem
Memphis
Persepolis

Hattuscha
Hethitisch
Ostsemitisch
Akkadisch
Jamchad
(Aleppo)
Ugarit
Ebla
Kition
Hama
(Larnaka)
Tadmor (Palmyra)
Kanaanaisch
Mari
Tyros
Damaskus
Westsemitisch
Aschkelon
Amman
Gaza
Jerusalem
Assur
Babylon
Memphis
Persisch
Sumerisch
Persepolis
Ägyptisch

Alphabet
Hattuscha
Hethitisch
Ostsemitisch
Akkadisch
Jamchad
(Aleppo)
Ugarit
Ebla
Assur
Kition
Hama
(Larnaka)
Oatna
Tadmor (Palmyra)
Phönizisch
Mari
Tyros
Damaskus
Westsemitisch
Aschkelon
Babylon
Amman
Gaza
Jerusalem
Persisch
Memphis
Sumerisch
Persepolis
Ägyptisch

Hattuscha
Hethitisch
Ostsemitisch
Akkadisch
Jamchad
(Aleppo)
Ugarit
Ebla
Assur
Kition
Hama
(Larnaka)
Oatna
Tadmor (Palmyra)
Phönizisch
Mari
Tyros
Damaskus
Westsemitisch
Babylon
Aschkelon
Amman
Gaza
Jerusalem
Persisch
Memphis
Sumerisch
Persepolis
Ägyptisch

Alphabet
Athen
Hattuscha
Griechisch
Aramäisch
Jamchad
Ugarit
(Aleppo)
Ebla
Hama
Assur
Kition
(Larnaka)
Qatna
Tadmor (Palmyra)
Byblos
Mari
Sidon
Damaskus
Tyros
Westsemitisch
Aschkelon
Amman
Babylon
Gaza
Jerusalem
Persisch
Memphis
Persepolis
Koptisch

Athen
Hattuscha
Griechisch
Syrisch
Jamchad
Ugarit
Kition
(Larnaka)
Byblos
Sidon
Tyros
Qatna
Tadmor (Palmyra)
Mari
Damaskus
Westsemitisch
Aschkelon
Amman
Gaza
Jerusalem
Babylon
Memphis
Hebräisch
Persisch
Persepolis
Koptisch
Aqaba
Dumah
Tabuk
Taima
Ha‘il
Dedan
Padakku
Hibra
Jadi‘u
Jatrib (Medina)
Arabisch
Südsemitisch
Tatlit
MA‘IN, SABA, QATABAN, HADRAMAWT

Griechisch
Athen
Hattuscha
Türkisch
Syrisch
Jamchad
(Aleppo)
Ugarit
Ebla
Kition
(Larnaka)
Hama
Qatna
Byblos
Tadmor (Palmyra)
Sidon
Mari
Tyros
Damaskus
Assur
Persisch
Samaria
Aschkelon
Amman
Gaza
Jerusalem
Babylon
Memphis
Hebräisch
Koptisch
Dumah
Aqaba
Persepolis
Tabuk
Taima
Ha‘il
Dedan
Padakku
Hibra
Jadi‘u
Jatrib (Medina)
Arabisch
Tatlit
MA‘IN↓, SABA↓, QATABAN↓, HADRAMAWT↓

PHILOSOPHIE
DEMOKRATIE
BIBEL
MONOTHEISMUS

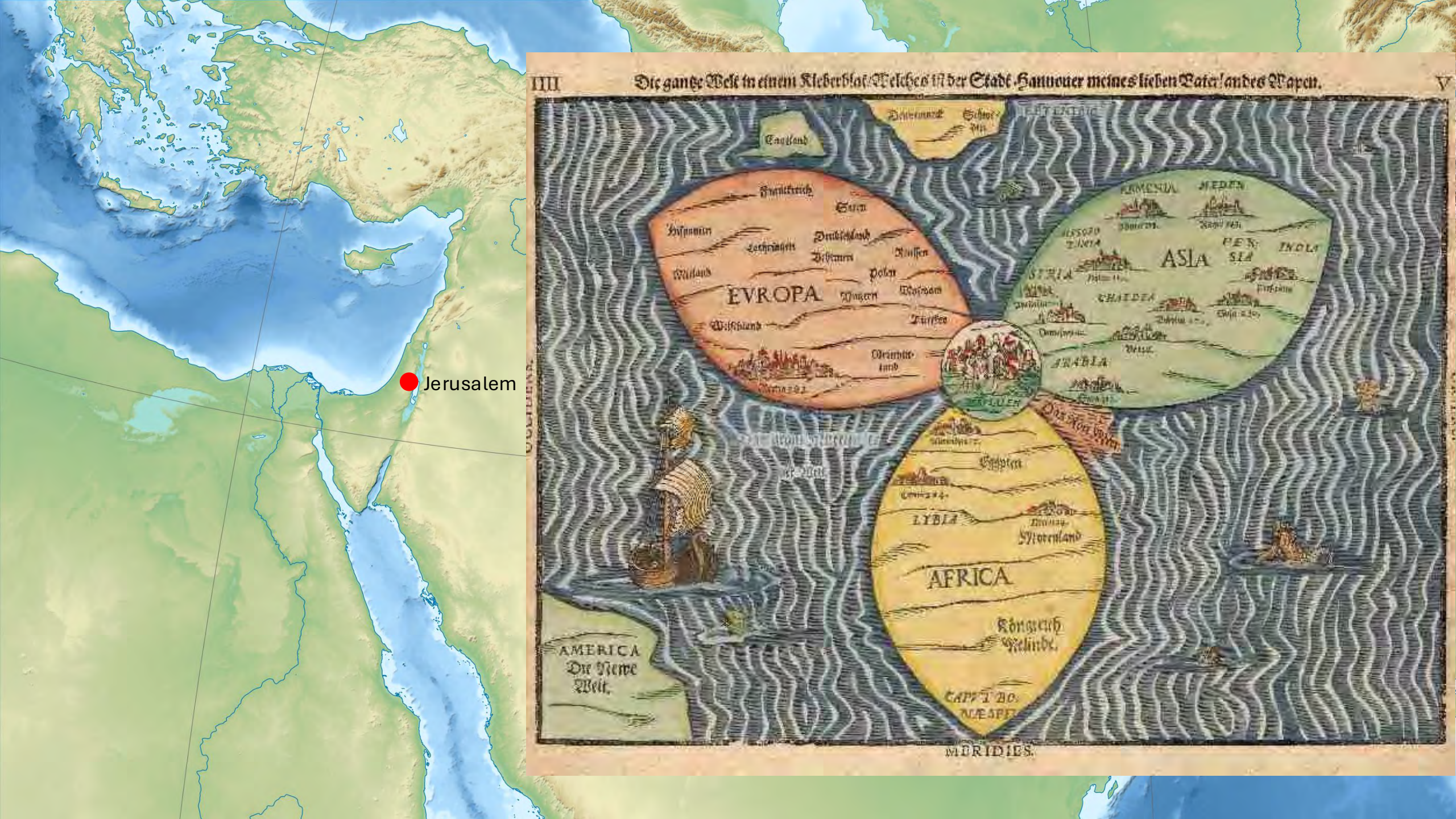
Jerusalem
IIII
Die gantze Welt in einem Kleberblat/Welches ist der Stadt Hannouer meines lieben Vaterlandes Wapen.
V
EVROPA
ASIA
AFRICA
AMERICA
Die Newe Welt.
MERIDIES.

Jerusalem

Deutsche Karte eines Teils des osmanischen Reiches

1855

Sykes-Picot-Abkommen

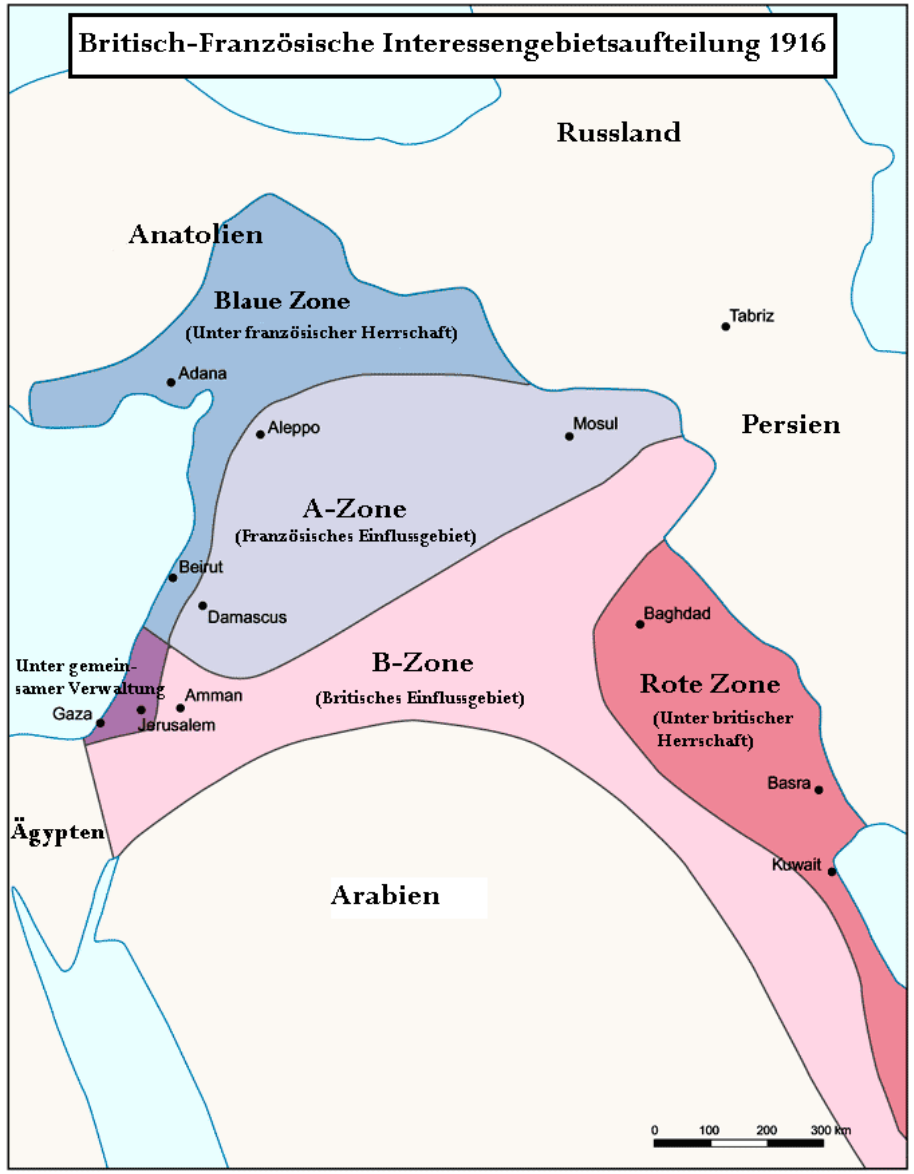

Der Vordere Orient nach der Konferenz in San Remo (1920)
von Frankreich verwaltete Gebiete
von Großbritannien verwaltete Gebiete
Britisches Protektorat
TÜRKEI
Alexandretta
Mosul
ZYPERN
Mittel-meer
SYRIEN (Fr.)
Beirut
LIBANON (Fr.)
IRAN (Persien)
Bagdad
Haifa
IRAK (Brit.)
PALÄSTINA (Brit.)
Amman
Jerusalem
ARABIEN
TRANS-JORDANIEN (Brit.)
ÄGYPTEN
Aqaba
Abadan
Basra
Persischer Golf
KUWAIT

RUSSIA
KAZAKHSTAN
UZBEKISTAN
TURKMENISTAN
TURKEY
GEORGIA
ARMENIA
AZERBAIJAN
IRAN
IRAQ
SYRIA
LEBANON
ISRAEL
JORDAN
CYPRUS
GREECE
BULGARIA
EGYPT
SAUDI ARABIA
KUWAIT
QATAR
BAHRAIN
UNITED ARAB EMIRATES
OMAN
YEMEN
SOMALIA
ETHIOPIA
ERITREA
DJIBOUTI
SUDAN
AFG.
PAK.
Black Sea
Caspian Sea
Mediterranean Sea
Red Sea
Persian Gulf
Arabian Sea
Gulf of Aden
Aegean Sea
Bucharest
Sofia
Varna
Constanta
Sevastopol'
Krasnodar
Groznyy
Sokhumi
Bat'umi
Tbilisi
Trabzon
Samsun
Bursa
Ankara
Istanbul
Thessaloniki
Athens
İzmir
Denizli
Konya
Kayseri
Antalya
İçel (Mersin)
Adana
Gaziantep
Erzurum
Diyarbakır
Van
Yerevan
Baku
Sumqayit
Türkmenbaşy
Balkanabat
Ashgabat
Mary
Turkmenabat
Nukus
Dasoguz
Tabriz
Rasht
Zanjān
Qazvīn
Tehran
Qom
Mashhad
Herāt
Kermānshāh
Arāk
Eşfahān
Ahvāz
Kermān
Zāhedān
Shīraz
Bandar-e Būshehr
Bandar 'Abbās
Abādān
Al Başrah
An Nāşiriyah
Mosul
Arbil
Kirkuk
Baghdad
Kuwait
Nicosia
Aleppo
Latakia
Ḥimş
Beirut
Damascus
Golan Heights
Tel Aviv-Yafo
Jerusalem
Amman
West Bank
Dead Sea
Port Said
Alexandria
Cairo
Al Jīzah
Gaza Strip
Suez
Al 'Aqabah
Tabūk
Asyūţ
Luxor
Aswān
Ḥafar al Bāţin
Ḥā'il
Al Jubayl
Ad Dammām
Dhahran
Manama
Buraydah
Riyadh
Doha
Abu Dhabi
Dubai
Muscat
Medina
Yanbu' al Baḥr
Ḥalā'ib
Jiddah
Mecca
Port Sudan
Abhā
Jīzān
Sanaa
Al Ḥudaydah
Al Mukallā
Al Ghayḍah
Ṣalālah
Ta'izz
Aden
Socotra (YEMEN)
Khartoum
Omdurman
Kassala
Wad Madani
Massawa
Asmara
Djibouti
Desē
Boosaaso
Berbera
Hargeysa
Dire Dawa
Addis Ababa
Scale 1:21,000,000
Lambert Conformal Conic Projection, standard parallels 12°N and 38°N
300 Kilometers
300 Miles
Boundary representation is not necessarily authoritative.
Golan Heights is Israeli-occupied Syria.
West Bank and Gaza Strip are Israeli-occupied with current status subject to the Israeli-Palestinian Interim Agreement -- permanent status to be determined through further negotiation.
Israel proclaimed Jerusalem as its capital in 1950, but the US, like nearly all other countries, maintains its Embassy in Tel Aviv.

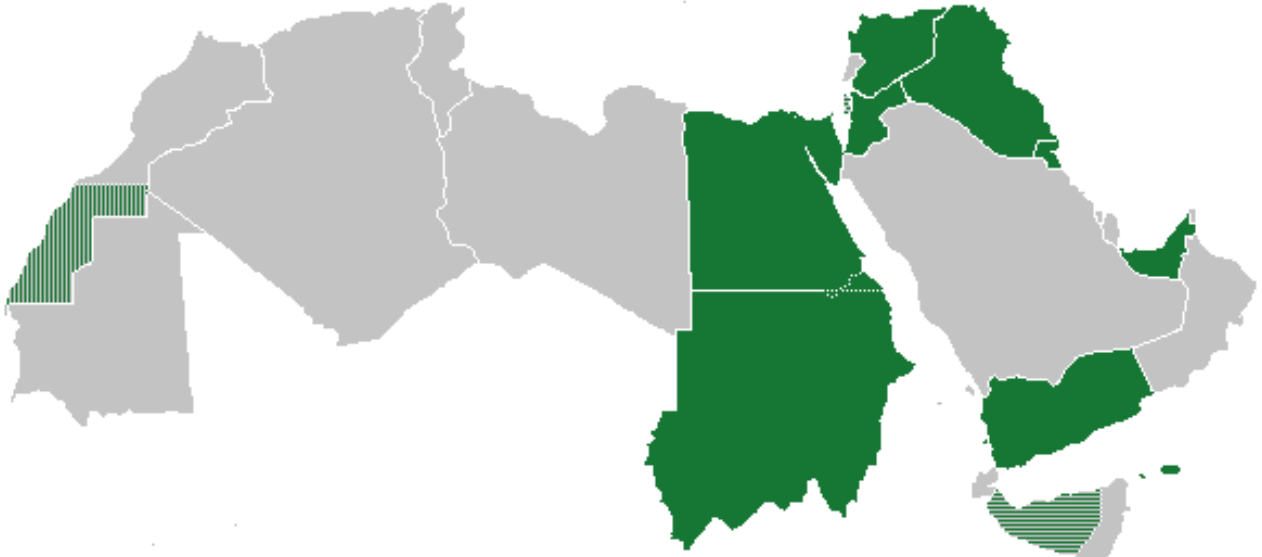

Middle East
Countries Flags
Bahrain
Cyprus
Egypt
Iraq
Iran
Israel
Jordan
Kuwait
Lebanon
Oman
Palestine
Qatar
Saudi Arabia
Syria
Turkey
United Arab Emirates
Yemen

Der Welthorizont der Jerusalemer Gelehrten nach Gen 10 («Völkertafel»)

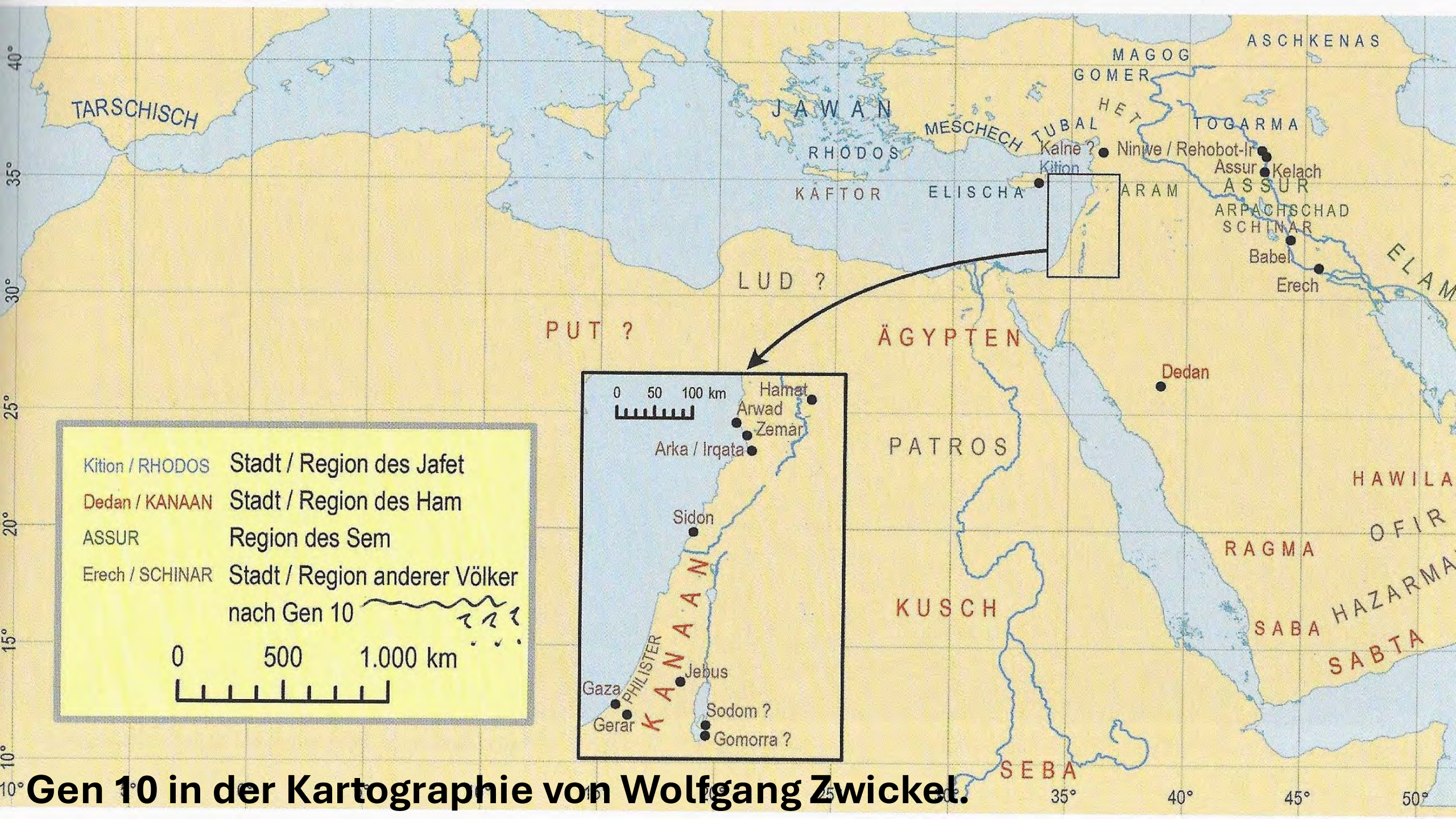

Gen 10 in der Kartographie von Wolfgang Zwickel.

Toledot: Israel und Kanaan (Gen 9-11)

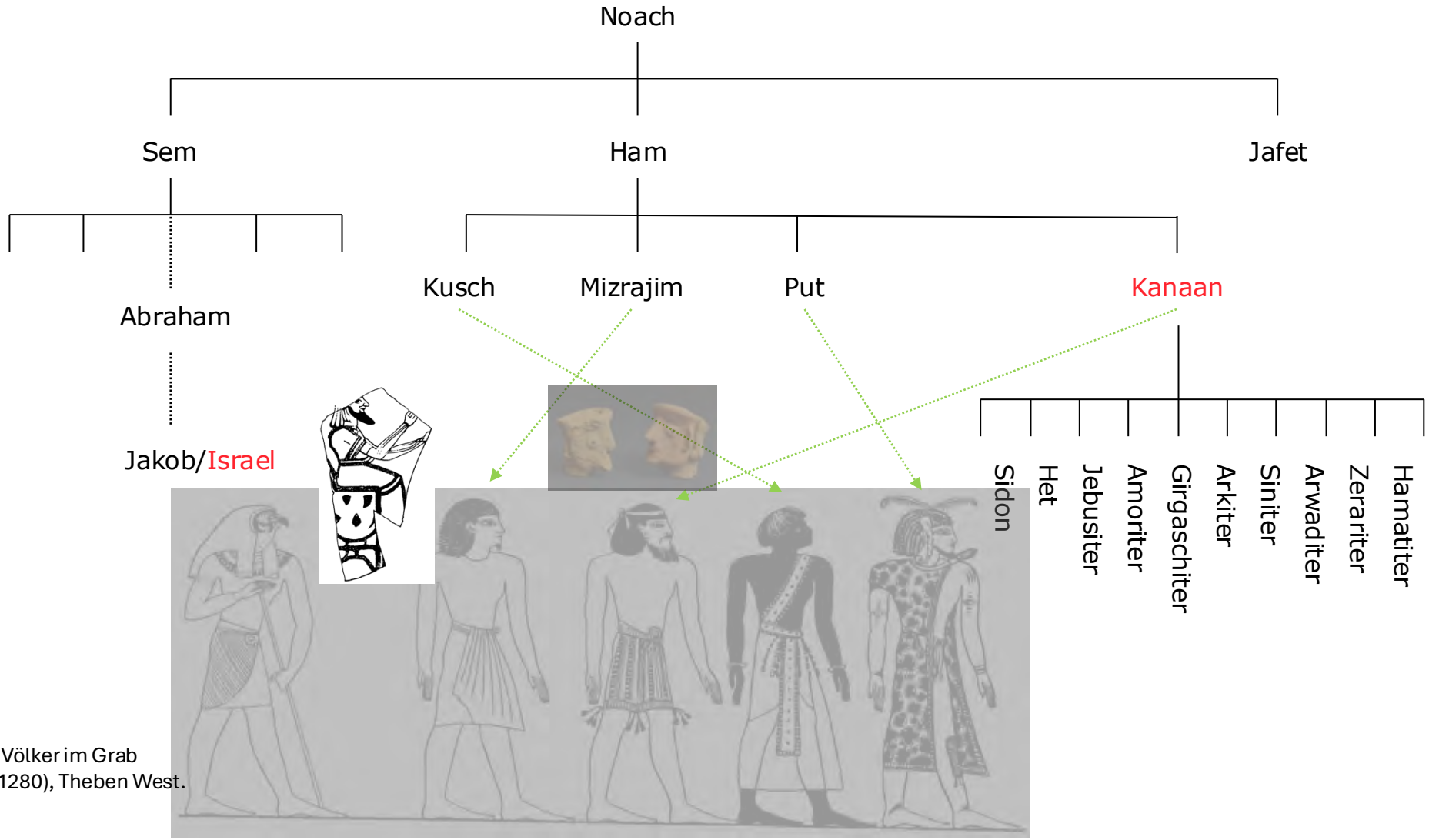

Re als Hirte der Völker im Grab Sethos I. (gest. 1280), Theben West.

Imperialer Wissenschaftskanon

Fazit

1. Die politische Landkarte des Nahen Ostens, aber auch unser Kanon der Geisteswissenschaften sind ein Produkt der europäischen Imperien.
2. Kanaan, bzw. Phönizien, anders umschrieben das westsemitische Sprachgebiet wurde nie in seiner Bedeutung als Hochkultur (Alphabet, Vertrag, Handel, Kunstvermittlung) erkannt und abgebildet.
3. Ein Grund dafür ist die Autorität der Bibel für das christliche Abendland und damit die bewusste oder unbewusste Adaption des biblischen Antikanaanismus.
4. Aber auch der osmanische (türkische) und der arabische Imperialismus haben zur Verdrängung des westsemitischen Kulturerbes beigetragen.
5. Die Kulturgeschichte der Levante wird bis heute mehrheitlich durch eine jüdisch-christlich gefärbte Brille gefiltert.
6. Eine Voraussetzung, um biblische Umwelt zu studieren, ist demnach die Überwindung biblischer und imperialer (westlicher, arabischer, türkischer) Vorurteile und Abwertungen.
7. Die Levante bzw. die westsemitische Koinê ist die nächste «Umwelt» der Bibel. Sie wird in meinen Kursen als ein eigenständiger, kreativer Kulturraum verstanden, der seinen Nachbarkulturen ebenbürtig ist und mit ihnen in vielfältigem Austausch stand, gebend und nehmend.